PORTFOLIO

Géomaticien/Analyste SIG

2025

Géomaticien/ Analyste SIG

1

2

3

4

5

6

7

8

9

Géomaticien-cartographe spécialisé dans l'analyse spatiale appliquée aux énergies renouvelables, avec une expertise sur la prospection territoriale aux ENR (éolien, solaire, agrivoltaïsme).

Maîtrise des outils SIG, notamment QGIS, pour la réalisation d'analyses multicritères intégrant des contraintes réglementaires, environnementales et territoriales. Capacité à automatiser les traitements SIG à l'aide de scripts Python (GeoPandas), afin de produire des résultats fiables, reproductibles et directement exploitables.

Méthodologie SIG multicritère pour l'identification des zones propices aux ENR

Identification de contraintes

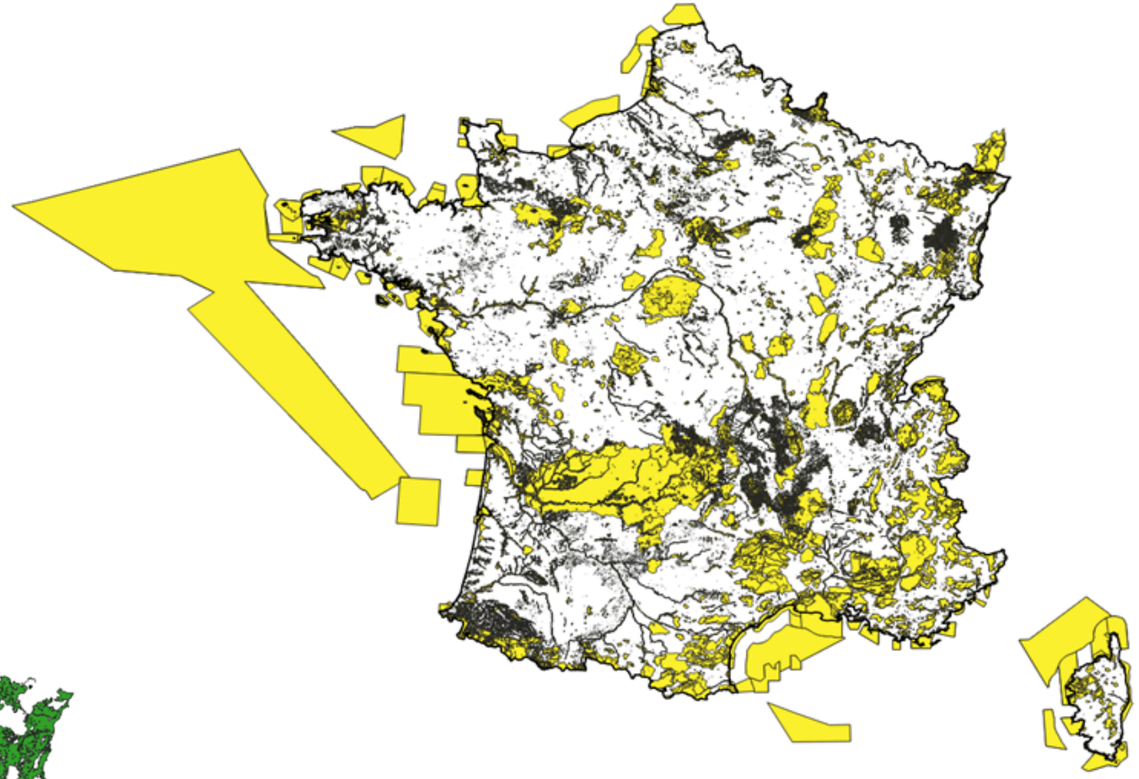

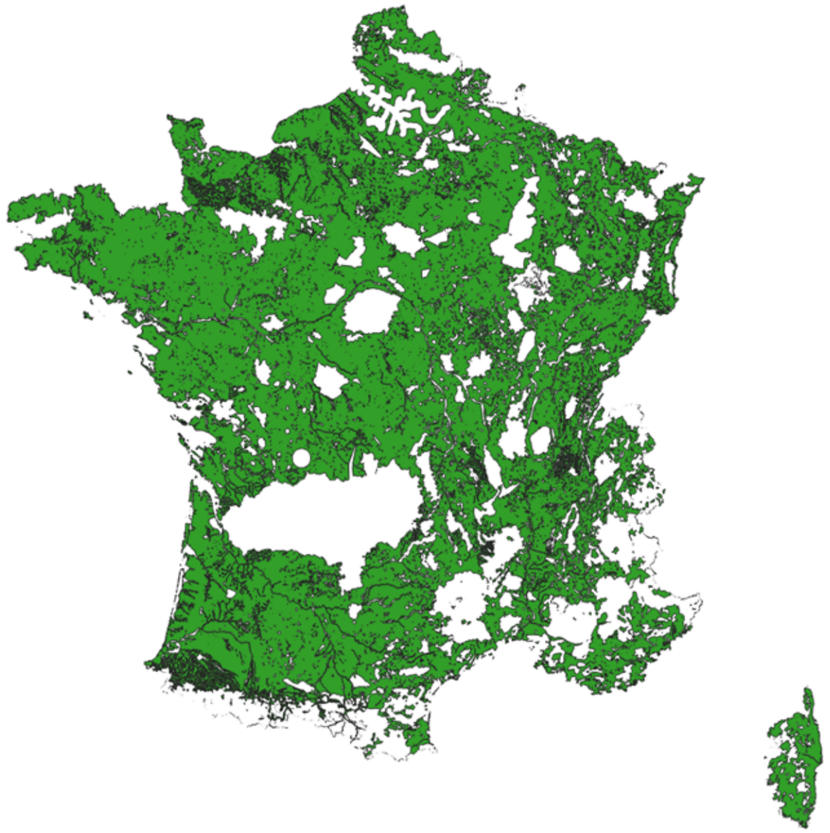

Filière éolienne



La méthodologie repose sur une analyse spatiale multicritère réalisée sous QGIS.

Les données réglementaires, environnementales et techniques ont été collectées, harmonisées et projetées dans un système de coordonnées commun.

Des zones d'exclusion et de contrainte ont été définies à partir des servitudes réglementaires (radars, aviation, zones protégées).

Les traitements SIG (tampons, différences, intersections) ont permis d'identifier les zones compatibles avec le développement des ENR.

Les résultats sont restitués sous forme de cartes thématiques d'aide à la décision.

zones coordinations radars militaires

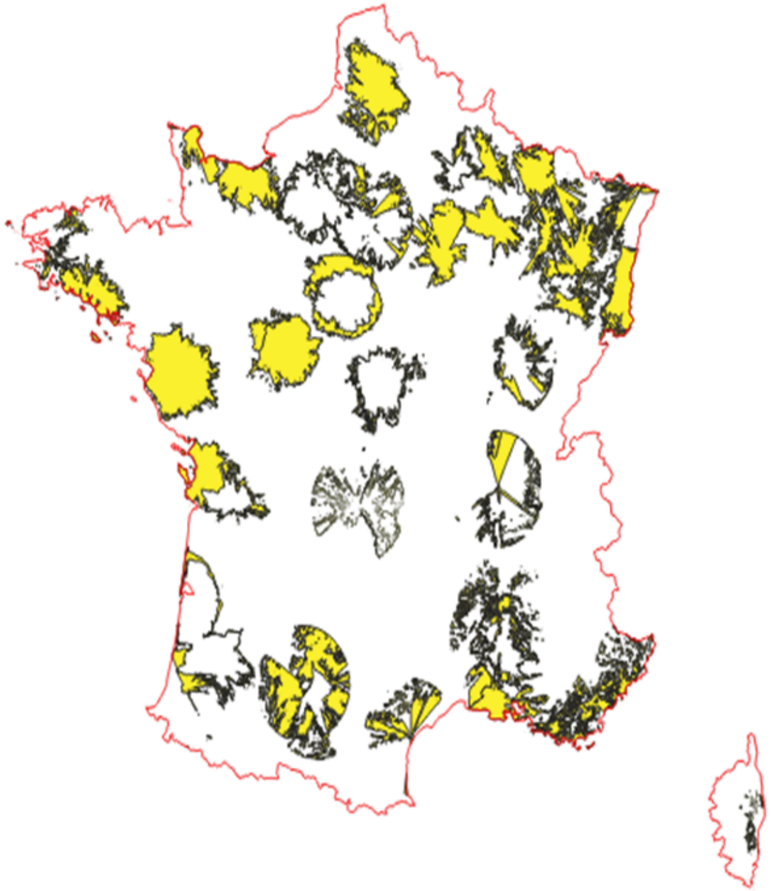

Modeleur Graphique eolienne

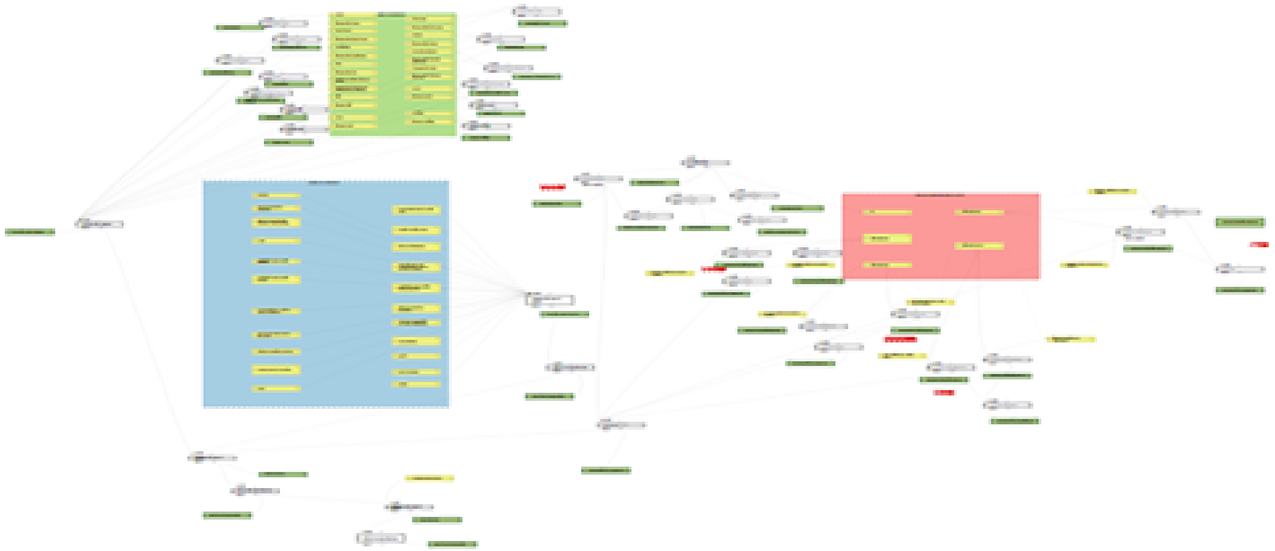

Modeleur Graphique PV et AgriPV

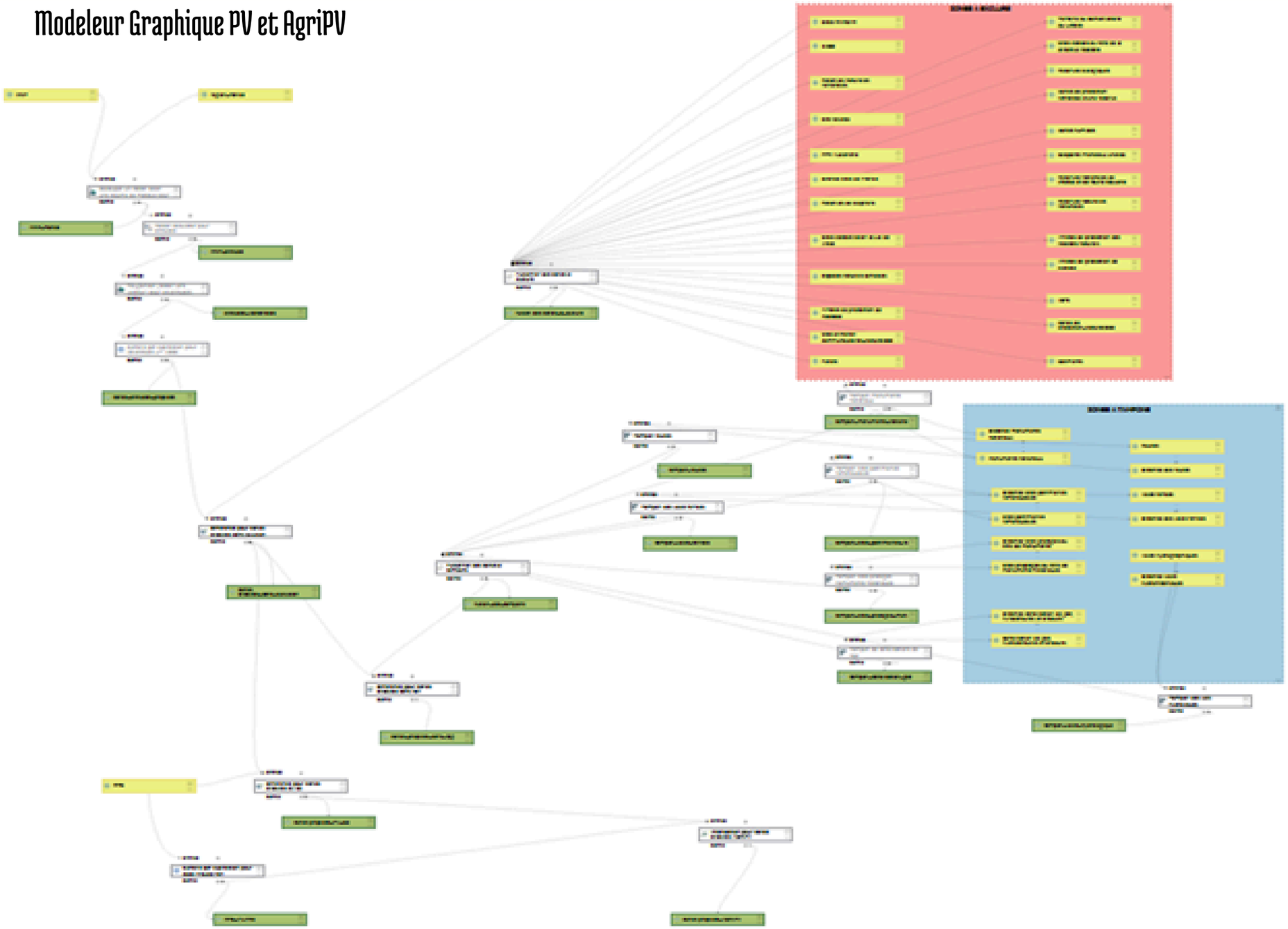

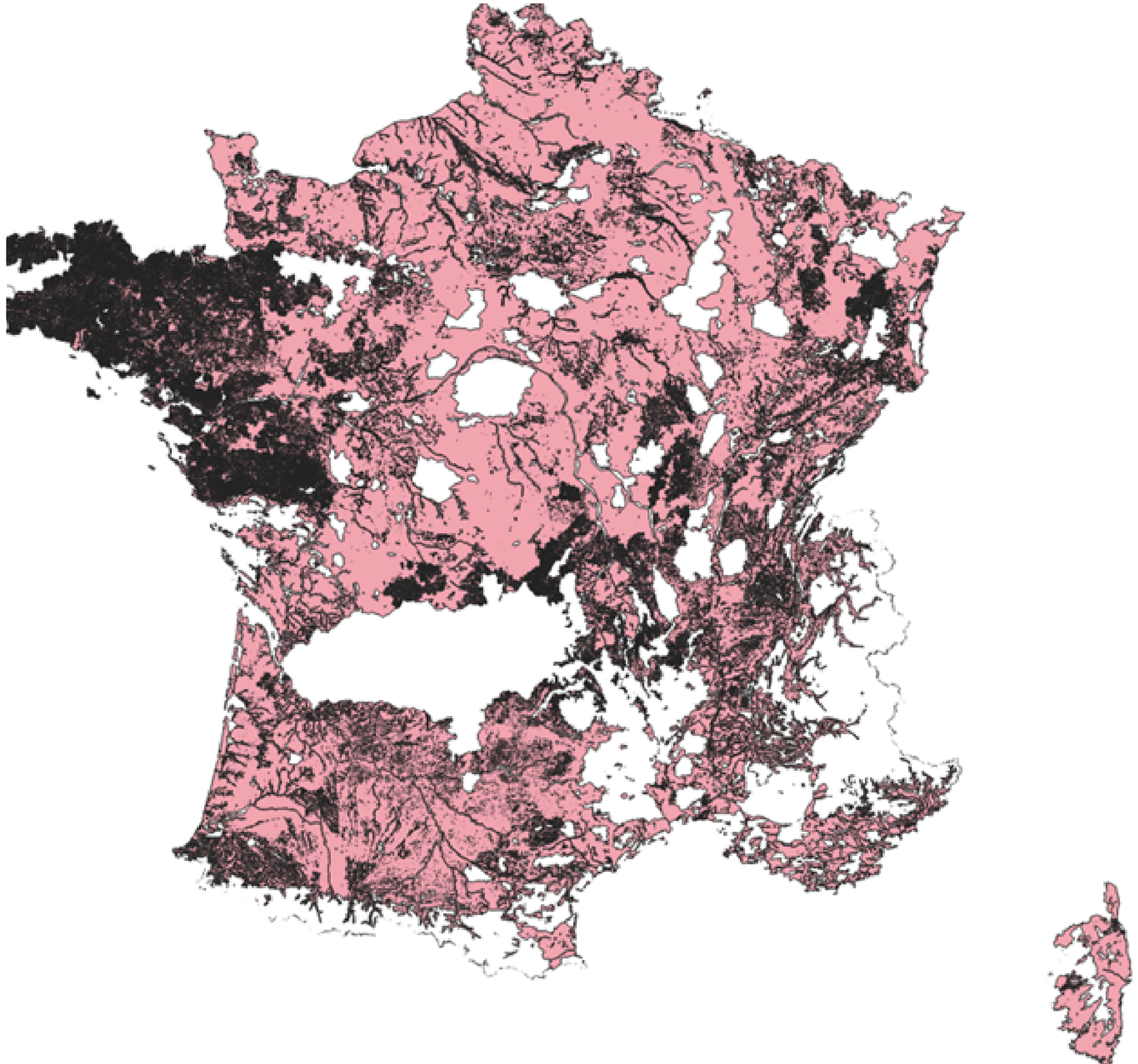

Contacts

Phone : *0601016321*

Email : *nourousaidou@gmail.com*